

DELEGACIÓN DE GRANADA
La mensura de un terreno, sea o no protestada, no basta por sí sola para aprobar la posesión ni la propiedad del mismo terreno. La Mensura en juicio de propiedad servirá para resolver esta una vez que sea practicado conforme al CODIGO DE PROCEDIMIENTO. Arto. 1662 c
DIRECCIÓN GENERAL DE CATASTRO FÍSICO

INETER DGCF INSTITUTO NICARAGÜENSE DE ESTUDIOS TERRITORIALES DELEGACIÓN DE GRANADA

DIRECCIÓN GENERAL DE CATASTRO FÍSICO APROBADO DELEGACIÓN DE GRANADA

DEPARTAMENTO DE GRANADA MUNICIPIO DE GRANA

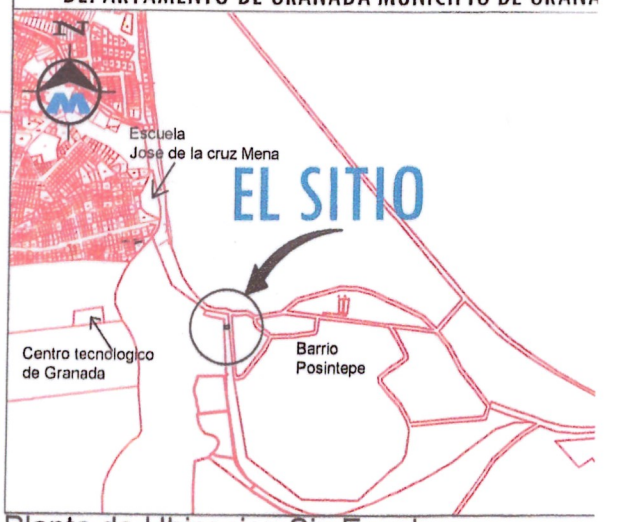

Planta de Ubicacion Sin Escala
Número Catastral:3051-4-09-000-06001

COORDENADAS NO VINCULADAS A LA RED GEODESICA DE NICARAGUA

CUADRO DE CONSTRUCCION

LADO EST	LADO PV	RUMBO	DISTANCIA	V	COORDENAD Y	COORDENAD X
				1	1,316,561.9484	614,159.
1	2	S 05°59'43.58" E	7.632	2	1,316,554.3579	614,160.
2	3	S 88°30'07.84" W	14.467	3	1,316,553.9798	614,145.
3	4	N 01°49'40.99" E	6.997	4	1,316,560.9728	614,146.
4	1	N 85°50'55.04" E	13.477	1	1,316,561.9484	614,159.

SUPERFICIE = 101.925 m2

MORGAN
Servicios Topograficos
Ing Bosco Javier Morgan
Lic Catastral: BMM100426
Cel: 8883 7568

Objeto Lev: Venta de una parte Indivisa	Número Catastral:3051-4-09-000-06001	Fecha: 5 de Noviembre del 2025	FIRMA:
Enajenante: Reina Isabel Zambrana Cédula: 201-060169-0008Y Conocida Registral como: Reyna Isabel Sevilla Zambrana	Ubicación: Bo.Posintepe.De Donde fue puente de lata 1c al oeste, 29.60m al sur. Municipio de Granada. Dpto. Granada	Ejecuta: Ing.Bosco Javier Morgan Lic. Catastral: BMM100426 Cel: 8883-7568 Email: ingmorgan73@gmail.com servicios topograficos	
Adquiere: Ivania Vanessa Condega Cédula: 201-270177-0000S	Area: 101.925 m2 = 144.57vrs2	Escala: 1 / 300	

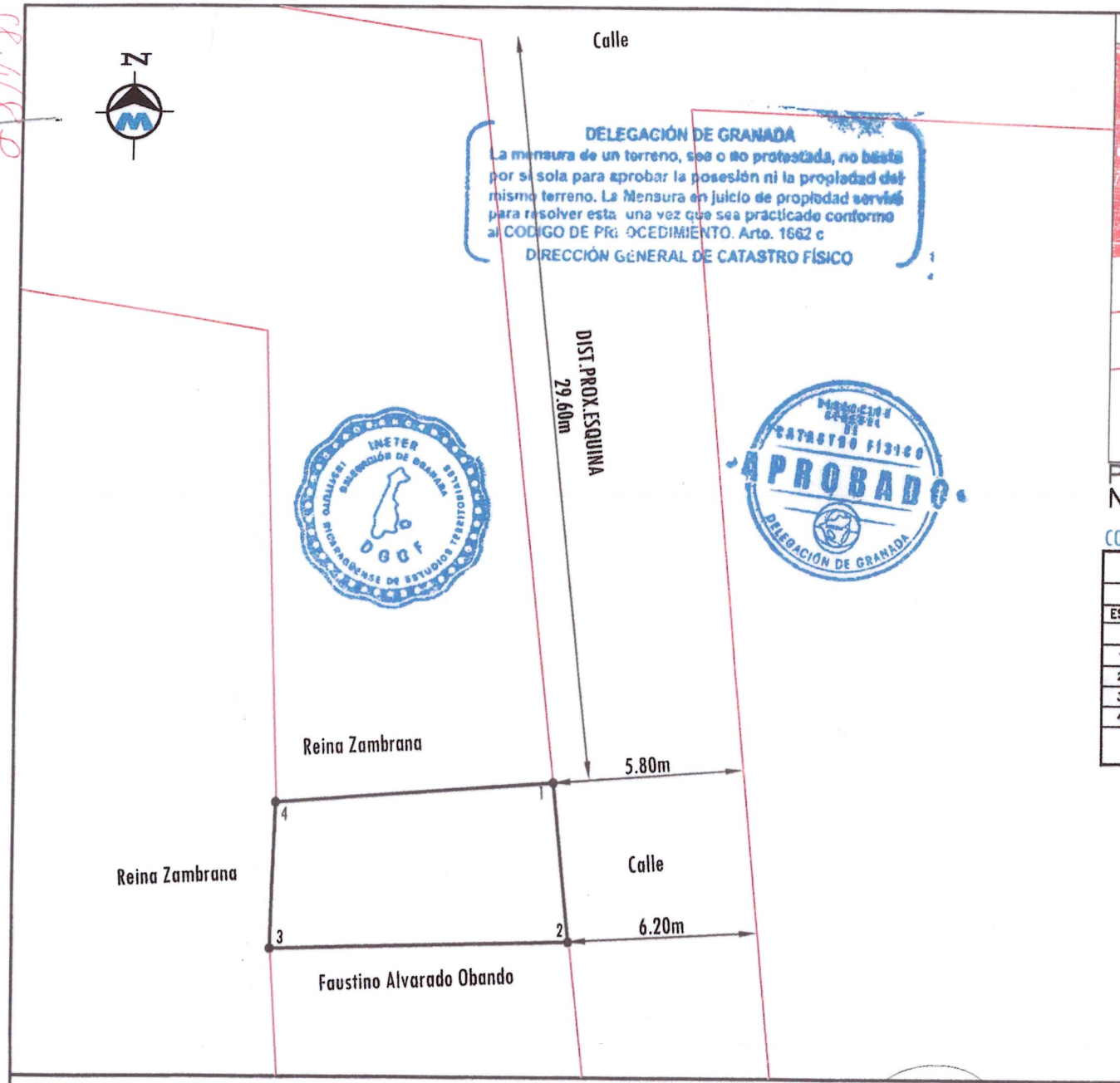

DELEGACIÓN DE GRANADA
La mensura de un terreno, sea o no protestada, no basta por sí sola para aprobar la posesión ni la propiedad del mismo terreno. La Mensura en juicio de propiedad servirá para resolver esta una vez que sea practicado conforme al CODIGO DE PROCEDIMIENTO. Arto. 1662 c
DIRECCIÓN GENERAL DE CATASTRO FÍSICO

INETER DELEGACIÓN DE GRANADA INSTITUTO NICARAGÜENSE DE ESTUDIOS TERRITORIALES DGGF

DIRECCIÓN GENERAL DE CATASTRO FÍSICO APROBADO DELEGACIÓN DE GRANADA

DEPARTAMENTO DE GRANADA MUNICIPIO DE GRANA

Planta de Ubicacion Sin Escala
Número Catastral:3051-4-09-000-06001

COORDENADAS NO VINCULADAS A LA RED GEODESICA DE NICARAGUA

CUADRO DE CONSTRUCCION

LADO EST	LADO PV	RUMBO	DISTANCIA	V	COORDENAD Y	COORDENAD X
				1	1,316,561.9484	614,159.
1	2	S 05°59'43.66" E	7.632	2	1,316,554.3579	614,160.
2	3	S 88°30'07.84" W	14.467	3	1,316,553.9798	614,145.
3	4	N 01°49'40.99" E	8.997	4	1,316,560.9728	614,146.
4	1	N 85°50'55.04" E	13.477	1	1,316,561.9484	614,159.

SUPERFICIE = 101.925 m2

MORGAN
Servicios Topograficos
Ing Bosco Javier Morgan
Lic Catastral: BMM100426
Cel: 8883 7568

Objeto Lev: Venta de una parte Indivisa	Número Catastral:3051-4-09-000-06001	Fecha: 5 de Noviembre del 2025	FIRMA:
Enajenante: Reina Isabel Zambrana Cédula: 201-060169-0008Y Conocida Registral como: Reyna Isabel Sevilla Zambrana	Ubicación: Bo.Posintepe.De Donde fue puente de lata 1c al oeste, 29.60m al sur. Municipio de Granada. Dpto. Granada	Ejecuta: Ing.Bosco Javier Morgan Lic. Catastral: BMM100426 Cel: 8883-7568 Email: ingmorgan73@gmail.com servicios topograficos	
Adquiere: Ivania Vanessa Condega Cédula: 201-270177-0000S	Area: 101.925 m2 = 144.57vrs2	Escala: 1 / 300	