

DEPARTAMENTO DE GRANADA MUNICIPIO DE GRANADA

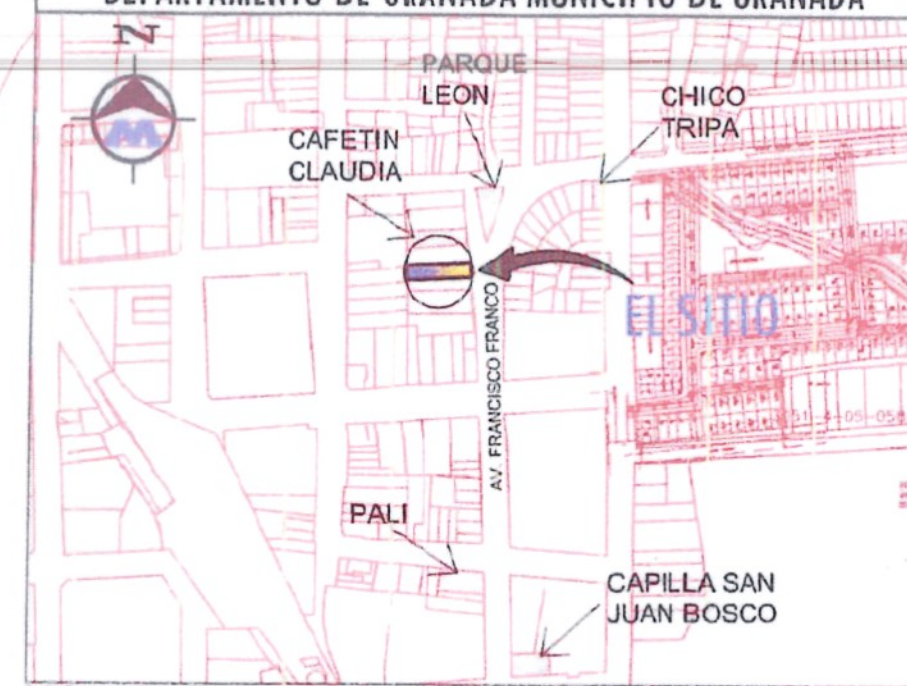

Número Catastral: 3051-4-05-048-13903
Planta de Ubicación Sin Escala

COORDENADAS NO VINCULADAS A LA RED GEODESICA DE NICARAGUA

CUADRO DE CONSTRUCCION

LADO EST	LADO PV	RUMBO	DISTANCIA	V	COORDENADAS Y	COORDENADAS X
				1	1,320,107.3887	613,954.3190
1	2	S 03°19'53.48" E	10.029	2	1,320,097.3766	613,954.9018
2	3	S 86°45'48.58" W	12.432	3	1,320,096.6747	613,942.4893
3	4	S 86°54'02.21" W	11.241	4	1,320,096.0669	613,931.2644
4	5	S 87°17'55.63" W	25.812	5	1,320,094.8505	613,905.4810
5	6	N 00°19'53.01" W	10.056	6	1,320,104.9061	613,905.4229
6	7	N 87°10'59.67" E	26.829	7	1,320,106.2245	613,932.2195
7	8	N 87°11'41.17" E	11.919	8	1,320,106.8078	613,944.1238
8	1	N 86°44'20.56" E	10.212	1	1,320,107.3887	613,954.3190

SUPERFICIE: 495.210 m2 = 702.41 Vrs2

Objeto Lev: Mensura Judicial	Número Catastral: 3051-4-05-048-13903		FIRMA:
Propietario: Carlos José Marquéz Ced: 202-051040-0000W C.C. Carlos José Marquéz Leypón	Ubicación: Avenida Francisco Franco, Capilla San Juan Bosco 2½ c al Norte. Municipio de Granada, Departamento de Granada.		Ejecuta: Ing.Bosco Javier Morgan Lic. Catastral: BMM100426 Cel: 8883-7568 Email: ingmorgan73@gmail.com servicios topograficos
Factor de escala: 1.418415	Área: 495.21 m² = 702.41 Vrs²	Escala: 1 / 500	Fecha: 23 de Septiembre del 2025

Transacción	Cudoc	Objeto Plano	Área (m²)	No. Lote
T-46ENSP-001	0038726	RECTIFICACIÓN	495.21	
Parcela Objeto	63123090294219		Documento	W8BYN7W
No. Licencia: BMM100426	Fecha Aprobación: 21/10/2025		Fecha Vencimiento: 21/10/2026	

DEPARTAMENTO DE GRANADA MUNICIPIO DE GRANADA

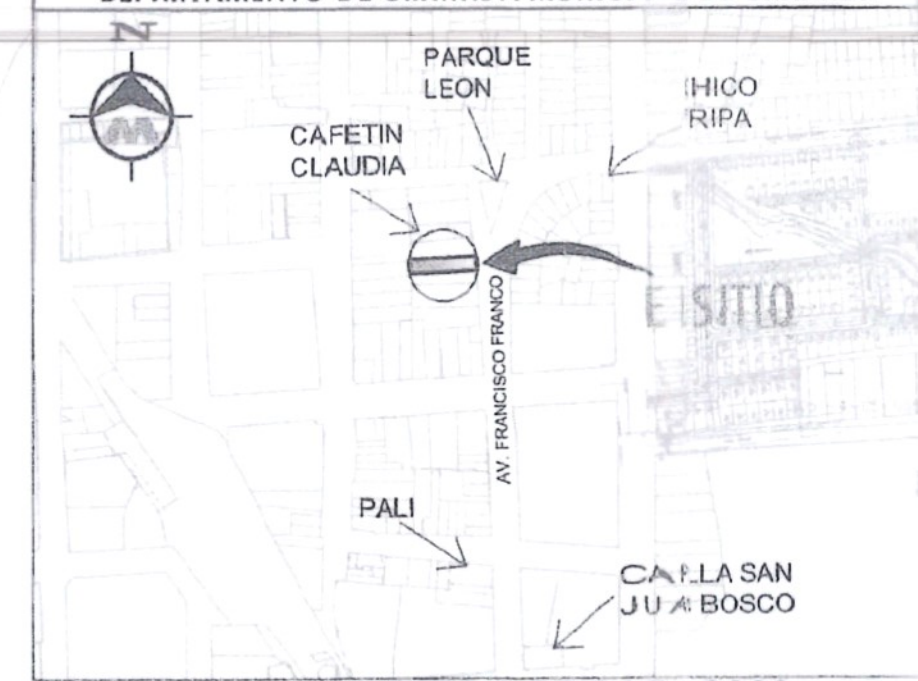

Número Catastral: 3051-4-05-048-13903
Planta de Ubicación Sin Escala

COORDENADAS NO VINCULADAS A LA RED GEODÉSICA DE NICARAGUA

CUADRO DE CONSTRUCCION

LADO EST	LADO PV	RUMBO	DISTANCIA	V	COORDENADAS Y	COORDENADAS X
				1	1,320,[illegible]3887	613,954.3190
1	2	S 03°19'53.48" E	10.029	2	1,320,[illegible]3766	613,954.9018
2	3	S 86°45'48.58" W	12.432	3	1,320,[illegible]8747	613,942.4893
3	4	S 86°54'02.21" W	11.241	4	1,320,[illegible]0669	613,931.2644
4	5	S 87°17'55.63" W	25.812	5	1,320,[illegible]8505	613,905.4810
5	6	N 00°19'53.01" W	10.056	6	1,320,[illegible]9061	613,905.4229
6	7	N 87°10'59.67" E	26.829	7	1,320,[illegible]2245	613,932.2195
7	8	N 87°11'41.17" E	11.919	8	1,320,[illegible]8078	613,944.1238
8	1	N 86°44'20.56" E	10.212	1	1,320,[illegible]3887	613,954.3190
SUPERFICIE: 495.210 m2 = 702.41 Vrs2						

Objeto Lev: Mensura Judicial	Número Catastral: 3051-4-05-048-13903		FIRMA:
Propietario: Carlos José Marquéz Ced: 202-051040-0000W C.C. Carlos José Marquéz Leypón	Ubicación: Avenida Francisco Franco, Capilla San Juan Bosco 2½ c al Norte. Municipio de Granada, Departamento de Granada.		Ejecuta: Ing.Bosco Javier Morgan Lic. Catastral: BMM100426 Cel. 8883-7568 Email: ingmorgan73@gmail.com servicios topograficos
Factor de escala: 1.41[illegible]15	Área: 495.21 m² = 702.41 Vrs²	Escala: 1 / 500	Fecha: 23 de Septiembre del 2025

Objeto Plano	Cudoc	Transacción	No. Lote
RECTIFICACIÓN	0038726	T-46ENSP-001	Area
63123090294219		Parcela Objeto	495.21
			Documento
			W8BYN7W
Fecha Aprobación: 21/10/2025		No. Licencia: BMM100426	Fecha Vencimiento: 21/10/2026

Objeto Lev: Mensura Judicial
Número Catastral: 3051-4-05-048-13903

Fecha: 23 de Septiembre del 2025

COORDENADAS NO VINCULADAS A LA RED GEODESICA DE NICARAGUA

CUADRO DE CONSTRUCCION

LADO		RUMBO	DISTANCIA	V	COORDENADAS	
EST	PV				Y	X
				1	1,320,107.3887	613,954.3190
1	2	S 03°19'53.48" E	10.029	2	1,320,097.3766	613,954.9018
2	3	S 86°45'48.58" W	12.432	3	1,320,096.6747	613,942.4893
3	4	S 86°54'02.21" W	11.241	4	1,320,096.0669	613,931.2644
4	5	S 87°17'55.63" W	25.812	5	1,320,094.8505	613,905.4810
5	6	N 00°19'53.01" W	10.056	6	1,320,104.9061	613,905.4229
6	7	N 87°10'59.67" E	26.829	7	1,320,106.2245	613,932.2195
7	8	N 87°11'41.17" E	11.919	8	1,320,106.8078	613,944.1238
8	1	N 86°44'20.56" E	10.212	1	1,320,107.3887	613,954.3190

SUPERFICIE: 495.210 m2 = 702.41 Vrs2

Ejecuta: Ing.Bosco Javier Morgan
Lic. Catastra: BMM100426
Cel: 8883-7568 Email: ingmorgan73@gmail.com
servicios topograficos

MORGAN
Servicios Topograficos
Ing Bosco Javier Morgan
Lic Catastral BMM100426
Cel: 8883 7568 T

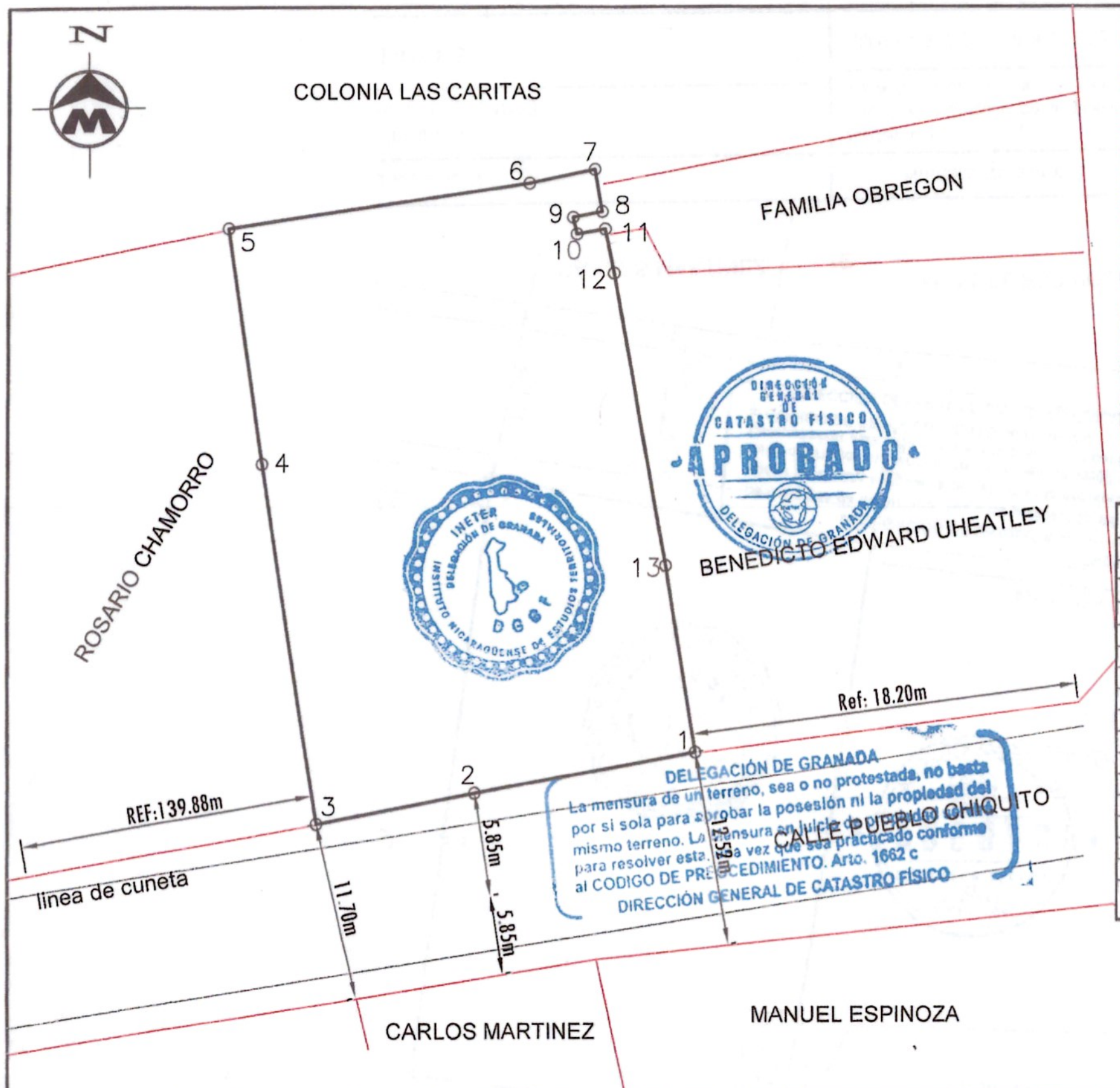

DEPARTAMENTO DE GRANADA MUNICIPIO DE GRA

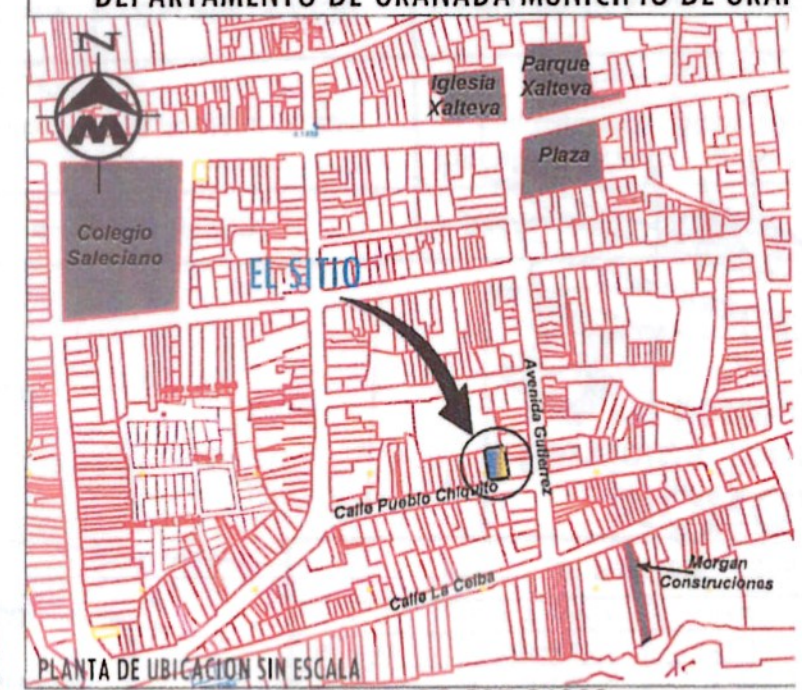

PLANTA DE UBICACION SIN ESCALA

Numero Catastral: 3051-4-05-087-01903

COORDENADAS NO VINCULADAS AL SISTEMA NACIONAL DE COORDENADAS

CUADRO DE CONSTRUCCION

LADO EST	LADO PV	RUMBO	DISTANCIA	V	COORDENA Y	
				1	1,318,569.6350	613
1	2	S 79°36'57.50" W	10.649	2	1,318,567.7156	613
2	3	S 79°13'13.09" W	7.630	3	1,318,566.2885	613
3	4	N 06°47'59.62" W	17.098	4	1,318,583.1853	613,
4	5	N 08°29'26.69" W	11.151	5	1,318,594.2141	613,
5	6	N 81°35'08.28" E	14.491	6	1,318,596.3346	613,
6	7	N 78°19'25.00" E	3.160	7	1,318,596.9741	613,
7	8	S 10°00'18.96" E	2.019	8	1,318,594.9862	613,
8	9	S 78°55'36.69" W	1.392	9	1,318,594.7188	613,
9	10	S 13°40'01.00" E	0.804	10	1,318,593.9378	613,
10	11	N 80°11'21.65" E	1.334	11	1,318,594.1650	613,
11	12	S 11°58'52.17" E	2.107	12	1,318,592.1036	613,
12	13	S 10°09'44.87" E	13.942	13	1,318,578.3806	613,
13	1	S 09°12'17.75" E	8.860	1	1,318,569.6350	613,

SUPERFICIE = 502.629 m2

MORGAN
Servicios Topograficos
Ing Bosco Javier Morgan
Lic Catastral: BMM100426
Cel: 8883-7568 T

Objeto Lev: Mensura Judicial	Numero Catastral: 3051-4-05-087-01903		FIRMA:
Propietario: Nancy Bergman Cedula de residencia:03022004039	Ubicacion: Calle Pueblo Chiquito, de la iglesia de Xalteva 4c al Sur 18.20m Oeste. Municipio de Granada. Dpto Granada.		Ejecuta: Ing.Bosco Javier Morgan Lic. Catastral: BMM 100426 Celular: 8883-7568 SERVICIOS TOPOGRAFICOS
Factor de Escala: 1.418415	ÁREA= 502.629 m² = 712.93 vrs²	Escala: 1 /300	Fecha: 07 de Agosto del 2025

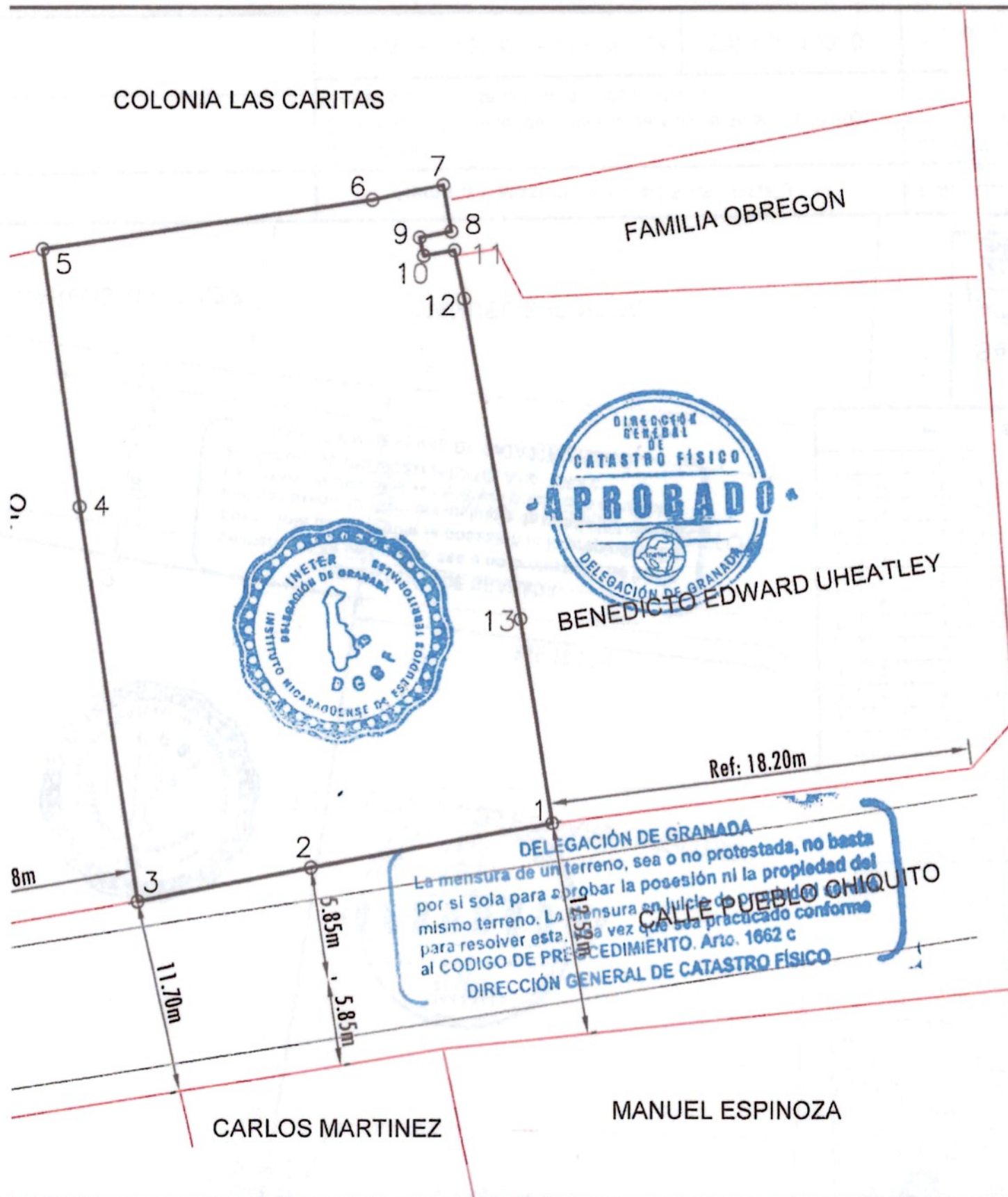

DEPARTAMENTO DE GRANADA MUNICIPIO DE GRANADA

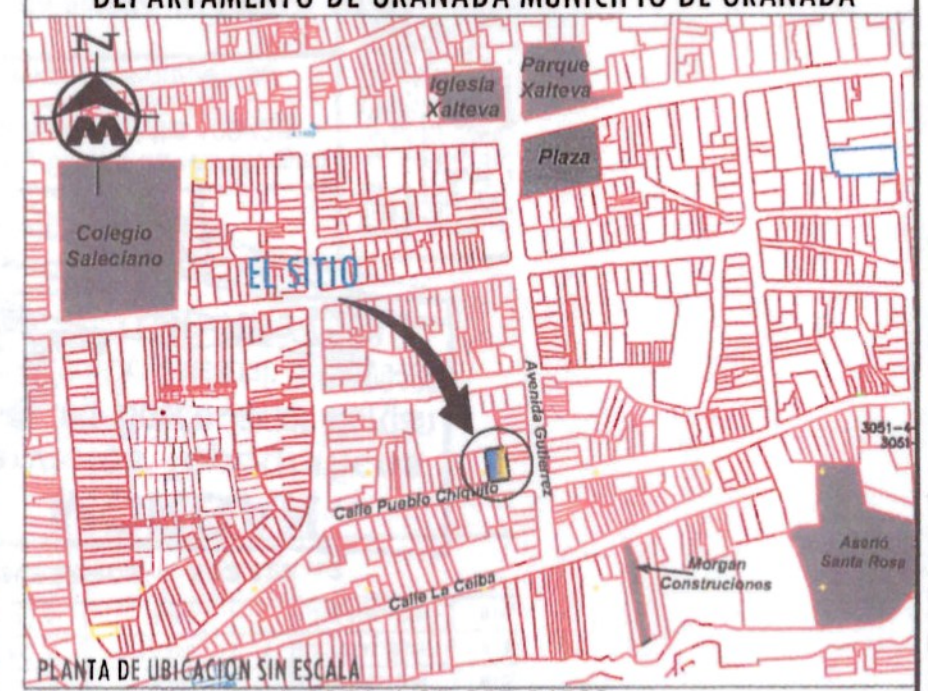

Numero Catastral: 3051-4-05-087-01903

COORDENADAS NO VINCULADAS AL SISTEMA NACIONAL DE COORDENADAS

CUADRO DE CONSTRUCCION

LADO EST	LADO PV	RUMBO	DISTANCIA	V	COORDENADAS Y	COORDENADAS X
				1	1,318,569.6350	613,180.5979
1	2	S 79°36'57.50" W	10.649	2	1,318,567.7156	613,170.1232
2	3	S 79°13'13.09" W	7.630	3	1,318,566.2885	613,162.6278
3	4	N 08°47'59.62" W	17.098	4	1,318,583.1853	613,160.0121
4	5	N 08°29'26.69" W	11.151	5	1,318,594.2141	613,158.3656
5	6	N 81°35'08.28" E	14.491	6	1,318,596.3346	613,172.7006
6	7	N 78°19'25.00" E	3.160	7	1,318,596.9741	613,175.7952
7	8	S 10°00'18.96" E	2.019	8	1,318,594.9862	613,176.1459
8	9	S 78°55'36.69" W	1.392	9	1,318,594.7188	613,174.7793
9	10	S 13°40'01.00" E	0.804	10	1,318,593.9378	613,174.9693
10	11	N 80°11'21.65" E	1.334	11	1,318,594.1650	613,176.2834
11	12	S 11°58'52.17" E	2.107	12	1,318,592.1036	613,176.7208
12	13	S 10°09'44.87" E	13.942	13	1,318,578.3806	613,179.1807
13	1	S 09°12'17.75" E	8.860	1	1,318,569.6350	613,180.5979

SUPERFICIE = 502.629 m2

MORGAN
Servicios Topograficos
Ing Bosco Javier Morgan
Lic Catastral: BMM100426
Cel: 8883 7568 T

ura Judicial	Numero Catastral: 3051-4-05-087-01903		FIRMA:
Bergman cia:03022004039	Ubicacion: Calle Pueblo Chiquito, de la iglesia de Xalteva 4c al Sur 18.20m Oeste. Municipio de Granada. Dpto Granada.		Ejecuta: Ing.Bosco Javier Morgan Lic. Catastral: BMM 100426 Celular 8883-7568 SERVICIOS TOPOGRAFICOS
1.418415	ÁREA= 502.629 m² = 712.93 vrs²	Escala: 1 /300	Fecha: 07 de Agosto del 2025

Transacción	Cudoc	Objeto Plano	No. Lote
T-46EBMA-001	0038447	RECTIFICACIÓN	
Parcela Objeto		631138156516	Documento	W8BY8UR
No. Licencia: BMM100426	Fecha Aprobación: 11/9/2025		Área (m²) 502.62	Fecha Vencimiento: 11/9/2026