LOTIFICACION VILLA CANDELARIA

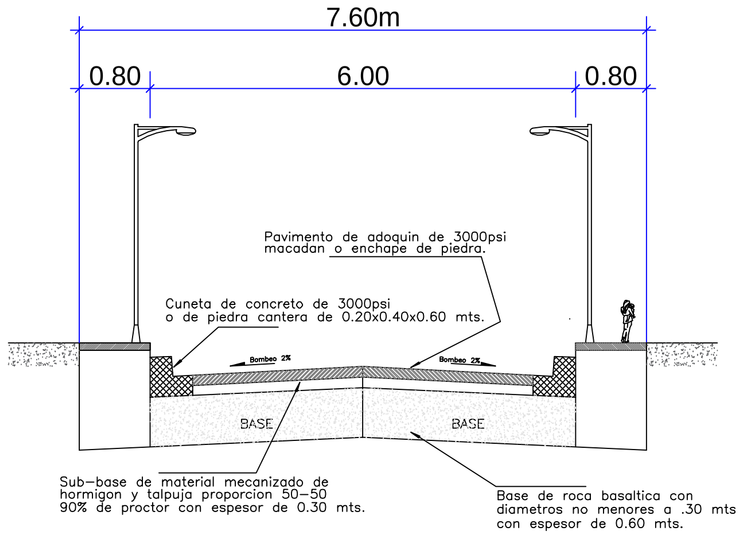

SECCION TIPICA DE CALLE

SIN ESCALA

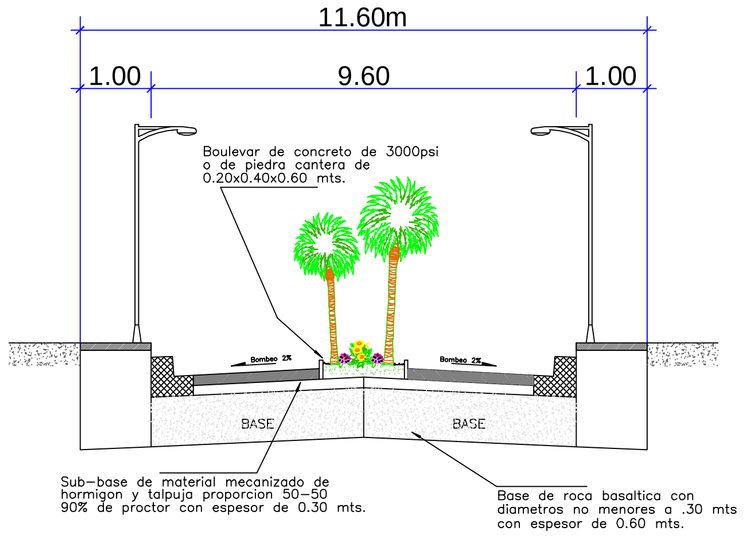

SECCION TIPICA DE CALLE CON BOULEVARD

SIN ESCALA

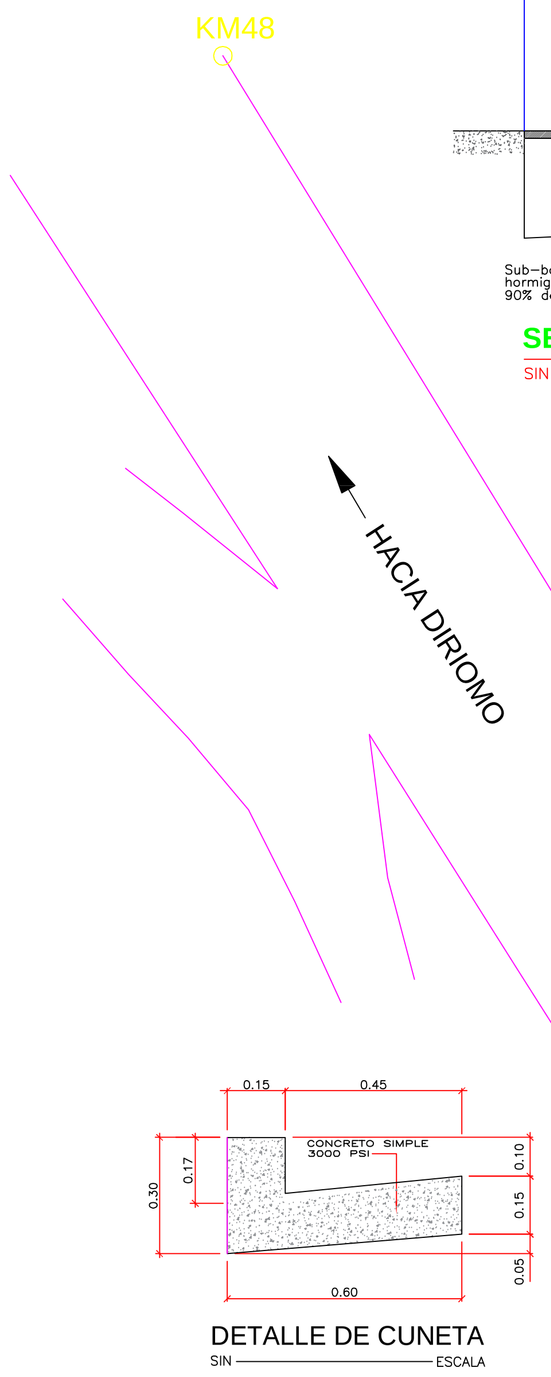

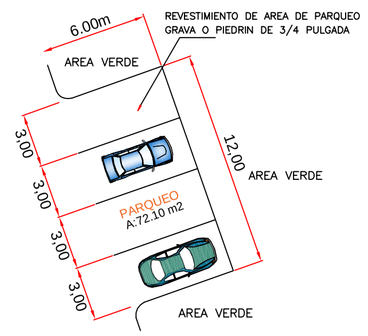

PARQUEO EN PLANTA

SIN ESCALA

Area Total del terreno: 9,321.84 mts2
Area de Calles y Andenes: 2,146.23 mts2
Area de Caseta:8.71 mts2
Area de Parqueo: 72.10 mts2
Area Total de Lotes: 6,296.095 mts2
Area Verde Total: 879.52 mts2 — 9%
Porcentaje de Area Construida:
Porcentaje de Area Libre: 33.2 %

GEOREFERENCIA:
X = 605,737.0000
Y=1,311,085.0000

DETALLE DE CUNETA

SIN ESCALA

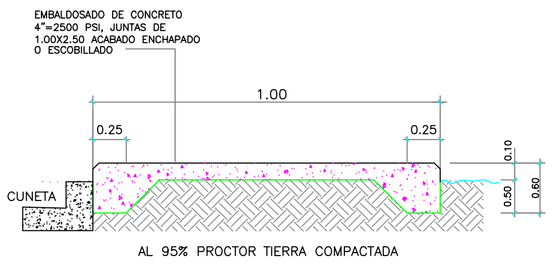

CORTE DE ANDEN D-1

SIN ESCALA

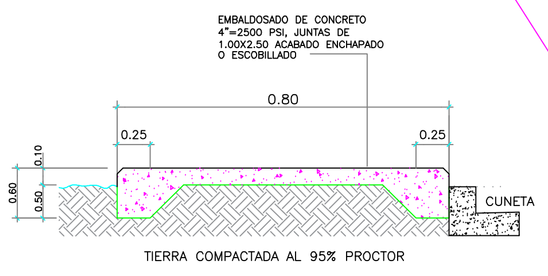

CORTE DE ANDEN D-2

SIN ESCALA

CUADRO DE DERROTERO CON COORDENADAS UTM, WGS84, Z-16 NO VINCULADA A LA RED NACIONAL DE GEODESIA

PLANTA DE UBICACION

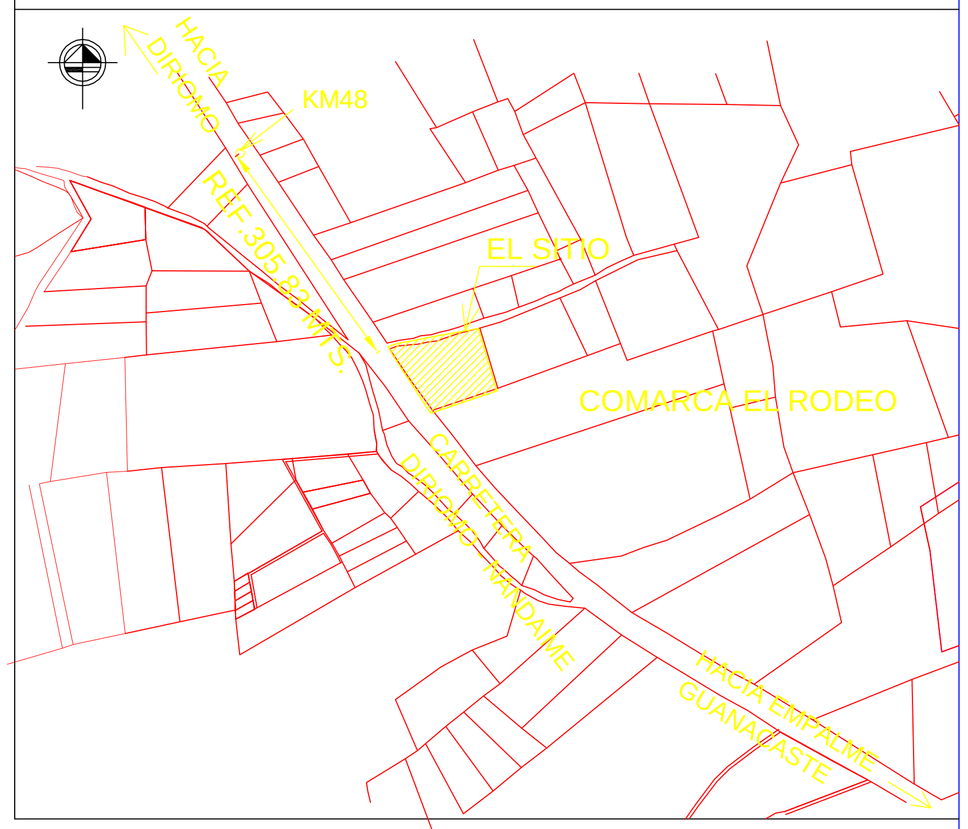

No.CAT. : 2951 - 1 - 16 - 000
DEL KM 48 CARRETERA DIRIOMO - NANDAIME, 305.83 MTS. SURESTE, COMARCA EL RODEO, MUNICIPIO DE DIRIOMO, DEPARTAMENTO DE GRANADA.

CUADRO DE DERROTERO

LADO EST	LADO PV	RUMBO	DIST.(M)	V	COORDENADAS Y	COORDENADAS X
				4	1,311,085.0000	605,737.0000
4	2	N 35°13'04" W	11.72	2	1,311,094.5780	605,730.2390
2	3	N 32°30'13" W	28.18	3	1,311,118.3460	605,715.0950
3	4	N 32°58'23" W	12.13	4	1,311,128.5180	605,708.4960
4	5	N 33°05'05" W	13.18	5	1,311,139.5600	605,701.3020
5	6	N 32°58'17" W	26.29	6	1,311,161.6150	605,686.9950
6	7	N 22°58'40" W	8.66	7	1,311,169.5840	605,683.6160
7	8	N 62°27'50" E	4.09	8	1,311,171.4750	605,687.2430
8	9	N 75°15'39" E	10.28	9	1,311,174.0900	605,697.1830
9	10	N 79°31'45" E	18.30	10	1,311,177.4150	605,715.1740
10	11	N 78°33'30" E	23.27	11	1,311,182.0320	605,737.9860
11	12	N 80°04'23" E	29.37	12	1,311,187.0960	605,766.9210
12	13	N 79°31'03" E	31.25	13	1,311,192.7810	605,797.6470
13	14	S 16°09'34" E	24.98	14	1,311,168.7920	605,804.5980
14	15	S 16°48'29" E	42.17	15	1,311,128.4270	605,816.7910
15	16	S 17°13'50" E	15.92	16	1,311,113.2240	605,821.5060
16	17	S 71°35'00" W	36.53	17	1,311,101.6830	605,786.8460
17	18	S 72°03'42" W	7.66	18	1,311,099.3230	605,779.5560
18	19	S 71°19'51" W	16.79	19	1,311,093.9470	605,763.6450
19	4	S 71°26'19" W	28.11	4	1,311,085.0000	605,737.0000

SUPERFICIE = 9,321.84 m2 = 13,222.10 vr2 = 1.3222 Mz

SELLO

Diseñado por: Ing.Bosco Javier Morgan M.
Lic. MTI:5365
Celular:8883-7568 Email:ingmorgan73@gmail.com

ESCALA: 1:1500

MORGAN CONSTRUCCIONES
Lic. MTI:5365 Lic. Catastral BMM-100426
Celular:8883-7568 Email:ingmorgan73@gmail.com

Contenido: LOTIFICACION VILLA CANDELARIA

Fecha: 31 DE JULIO 2022

AREA: 9,321.84 m2 = 13,222.10 vr2 = 1.3222 Mz

UBICACION: DEL KM 48 CARRETERA DIRIOMO - NANDAIME. 305.83 MTS. SURESTE, COMARCA EL RODEO, MUNICIPIO DE DIRIOMO, DEPARTAMENTO DE GRANADA.

Hoja:1

DERECHO DE AUTOR
Ningún cambio podrá realizarse en este plano sin la autorización por escrito del Ing. Bosco Javier Morgan. Prohibida la reproducción parcial o total de este diseno sin la autorización previa del Ing. Bosco Javier Morgan