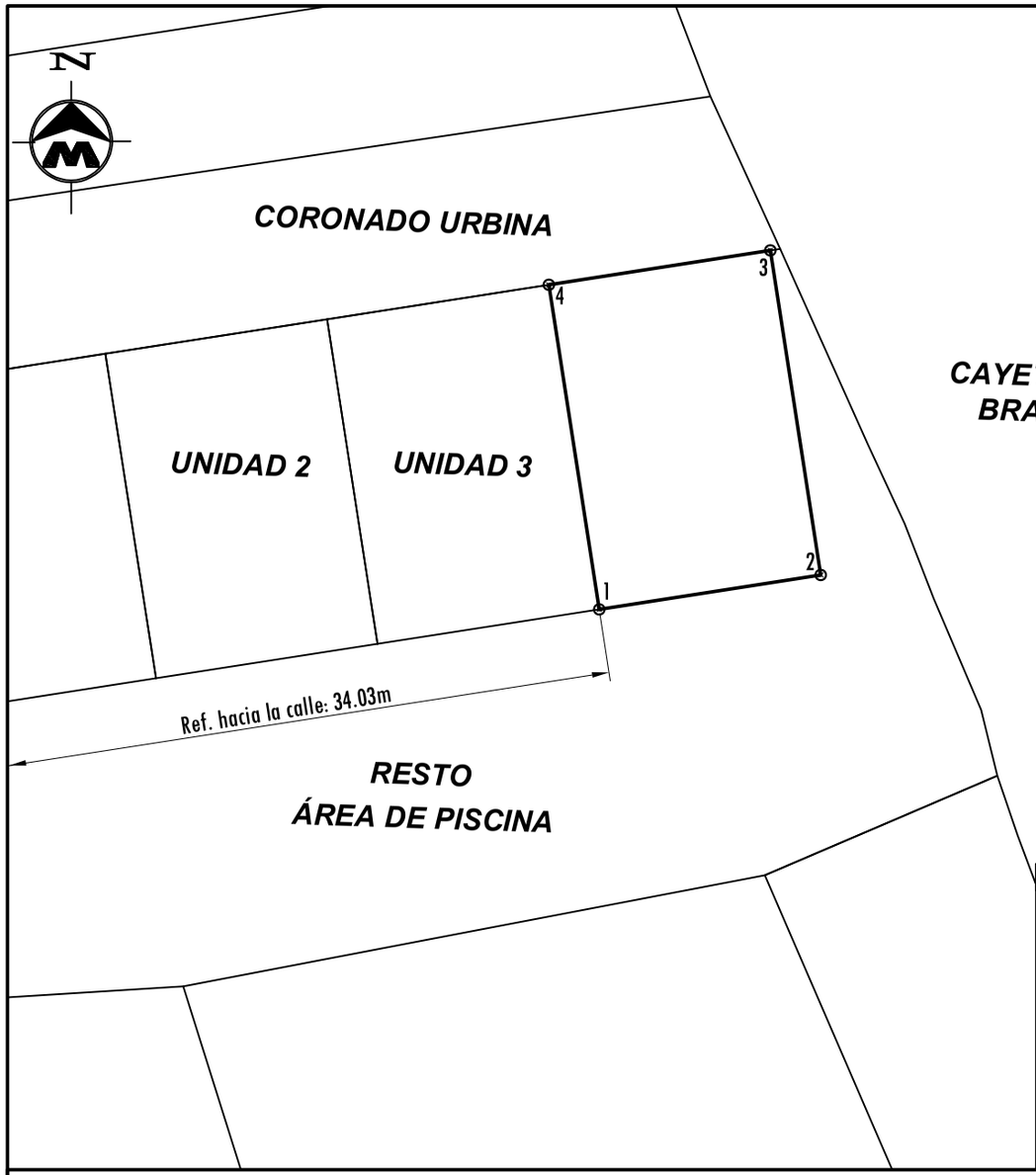

DEPARTAMENTO DE GRANADA MUNICIPIO DE GRANADA

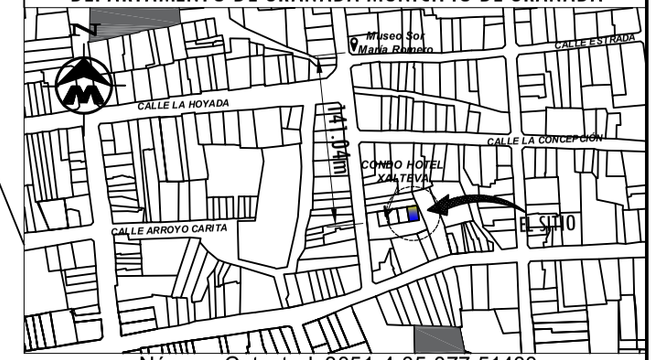

Número Catastral: 3051-4-05-077-51400
Planta de Ubicación Sin Escala

COORDENADAS NO VINCULADAS A LA RED GEODESICA DE NICARAGUA

CUADRO DE CONSTRUCCION

LADO EST	LADO PV	RUMBO	DISTANCIA	V	COORDENADAS Y	COORDENADAS X
				1	1,318,667.4729	613,449.0261
1	2	N 81°09'50.00" E	8.200	2	1,318,668.7325	613,457.1287
2	3	N 08°50'10.00" W	12.014	3	1,318,680.6035	613,455.2834
3	4	S 81°09'50.00" W	8.200	4	1,318,679.3439	613,447.1807
4	1	S 08°50'10.00" E	12.014	1	1,318,667.4729	613,449.0261

SUPERFICIE: 98.511 m2 = 139.73 Vrs2

ESQUEMA DE UBICACIÓN

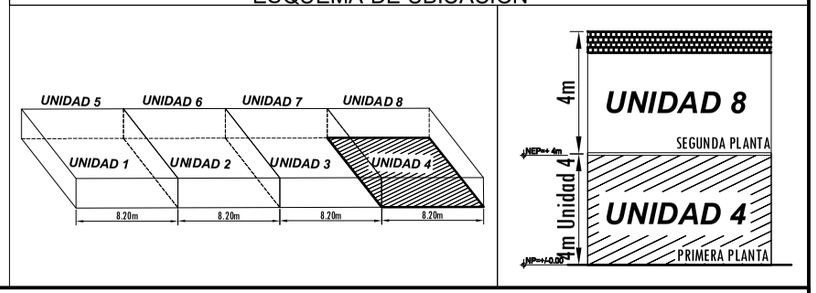

Objeto Lev: Desmembración	Número Catastral: 3051-4-05-077-51400		FIRMA:
Enajenante: DONALD JAY SNYDER Pasaporte USA: 521499712	Ubicación: Casa Museo Sor María Romero 141.04 m SE, Condominio Hotel Xalteva. Unidad 4. Municipio de Granada, Departamento de Granada.		Ejecuta: Ing.Bosco Javier Morgan Lic. Catastral: BMM100426 Cel: 8883-7568 Email: ingmorgan73@gmail.com
Adquirente: JEROME TOUBEAU Pasaporte: GA8672513	Área: 98.511 m² = 139.73 Vrs²	Escala: 1 / 250	Fecha: 28 de Mayo del 2025

ESPACIO PARA ESQUELA