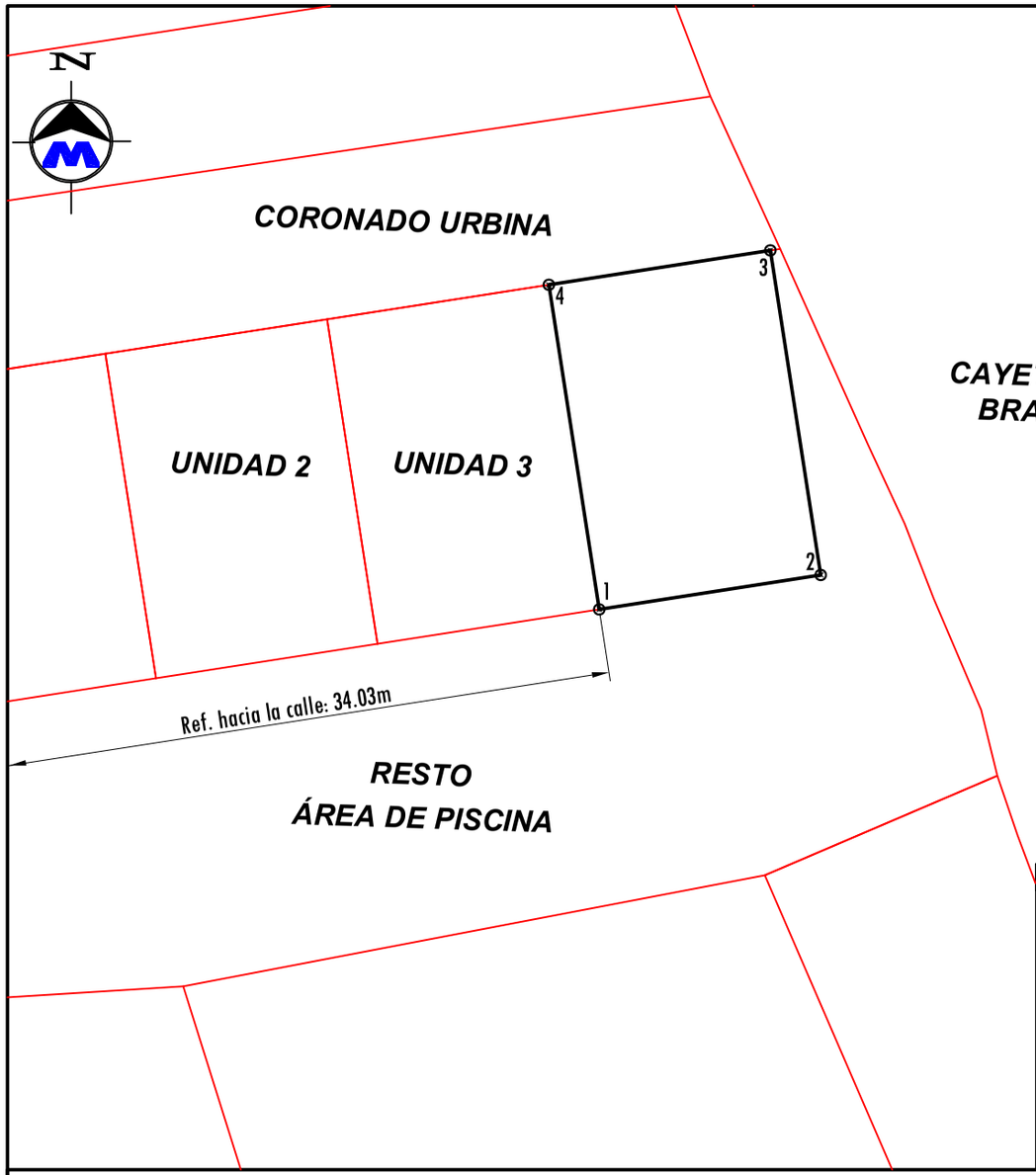


## DEPARTAMENTO DE GRANADA MUNICIPIO DE GRANADA

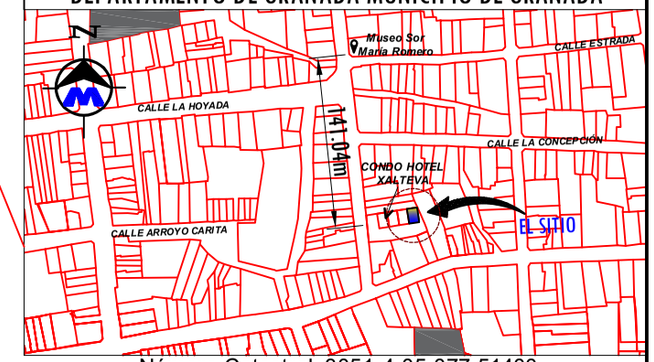


Número Catastral: 3051-4-05-077-51400
Planta de Ubicación Sin Escala

COORDENADAS NO VINCULADAS A LA RED GEODESICA DE NICARAGUA

**CUADRO DE CONSTRUCCION**

| LADO EST | LADO PV | RUMBO | DISTANCIA | V | COORDENADAS Y | COORDENADAS X |
|---|---|---|---|---|---|---|
| | | | | 1 | 1,318,667.4729 | 613,449.0261 |
| 1 | 2 | N 81°09'50.00" E | 8.200 | 2 | 1,318,668.7325 | 613,457.1287 |
| 2 | 3 | N 08°50'10.00" W | 12.014 | 3 | 1,318,680.6035 | 613,455.2834 |
| 3 | 4 | S 81°09'50.00" W | 8.200 | 4 | 1,318,679.3439 | 613,447.1807 |
| 4 | 1 | S 08°50'10.00" E | 12.014 | 1 | 1,318,667.4729 | 613,449.0261 |

**SUPERFICIE: 98.511 m2 = 139.73 Vrs2**

ESQUEMA DE UBICACIÓN

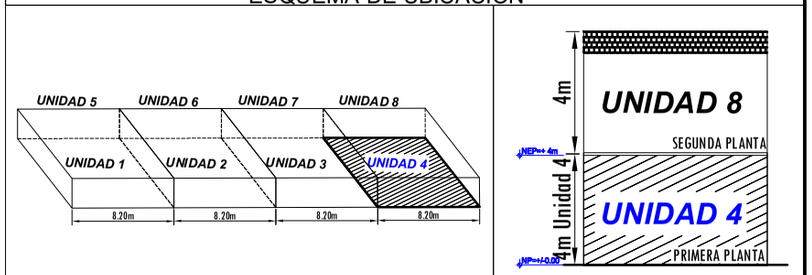


| | | |
|---|---|---|
| Objeto Lev: Desmembración | Número Catastral: 3051-4-05-077-51400 | FIRMA: |
| Enajenante: DONALD JAY SNYDER<br>Pasaporte USA: 521499712 | Ubicación: Casa Museo Sor María Romero 141.04 m SE, Condominio Hotel Xalteva. Unidad 4. Municipio de Granada, Departamento de Granada. | Ejecuta: Ing.Bosco Javier Morgan<br>Lic. Catastral: BMM100426<br>Cel: 8883-7568 Email: ingmorgan73@gmail.com |
| Adquirente: JEROME TOUBEAU<br>Pasaporte: GA8672513 | Área: 98.511 m² = 139.73 Vrs² — Escala: 1 / 250 | Fecha: 28 de Mayo del 2025 |

ESPACIO PARA ESQUELA