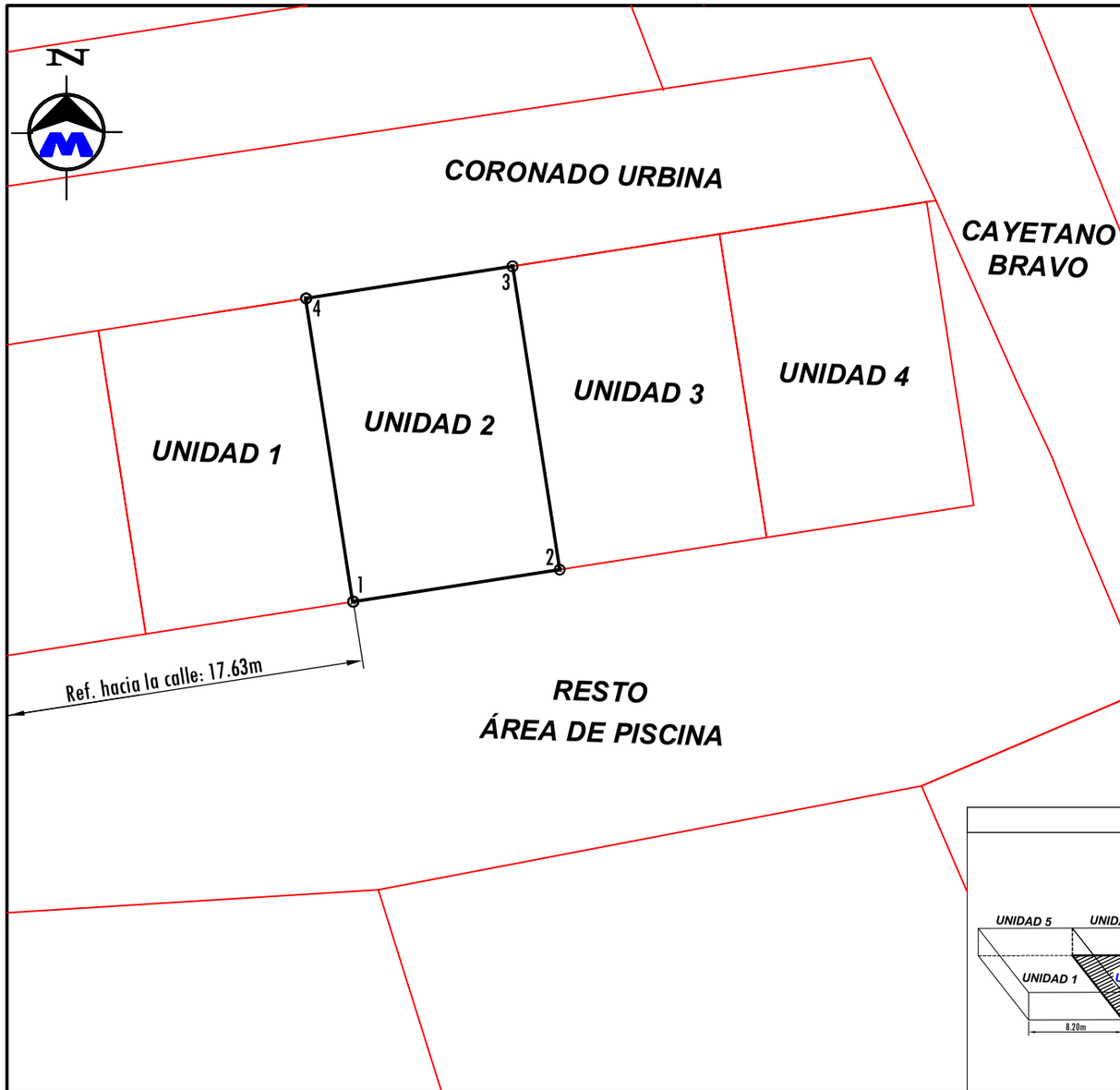

DEPARTAMENTO DE GRANADA MUNICIPIO DE GRANADA

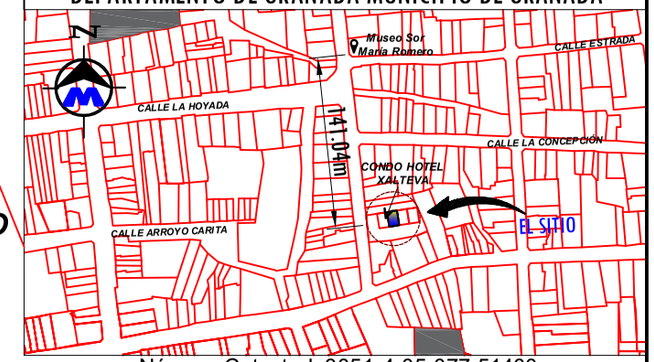

Número Catastral: 3051-4-05-077-51400
Planta de Ubicación Sin Escala

COORDENADAS NO VINCULADAS A LA RED GEODESICA DE NICARAGUA

DERROTERO

LINEA	RUMBO	DIST	COORD UTM
1-2	N81°09'41"E	8.20	16P 613432.82, 1318664.95
2-3	N08°50'20"W	12.01	16P 613440.92, 1318666.21
3-4	S81°10'02"W	8.20	16P 613439.08, 1318678.08
4-1	S08°50'01"E	12.01	16P 613430.98, 1318676.82

Área: 98.5134 m² = 139.7329 Vrs²

ESQUEMA DE UBICACIÓN

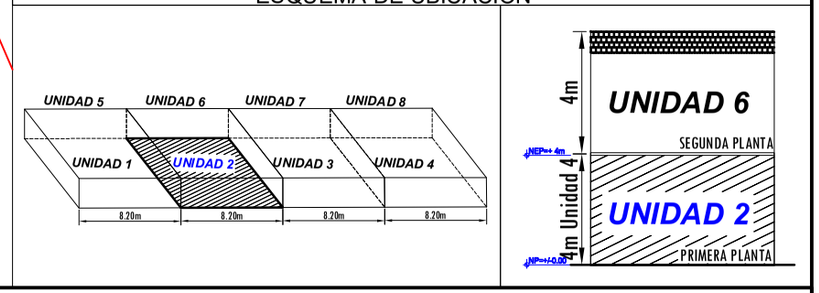

Objeto Lev: Desmembración	Número Catastral: 3051-4-05-077-51400	FIRMA:
Enajenante: DONALD JAY SNYDER Pasaporte USA: 521499712	Ubicación: Casa Museo Sor María Romero 141.04 m SE, Condominio Hotel Xalteva. Unidad 2. Municipio de Granada, Departamento de Granada.	Ejecuta: Ing.Bosco Javier Morgan Lic. Catastral: BMM100426 Cel: 8883-7568 Email: ingmorgan73@gmail.com
Adquirentes: SCOTT ANDREW HOROWITZ Pasaporte: 583132846 ANA HOROWITZ Pasaporte: A34627863	Área: 98.5134 m² = 139.7329 Vrs² — Escala: 1 / 250	Fecha: 28 de Mayo del 2025

ESPACIO PARA ESQUELA