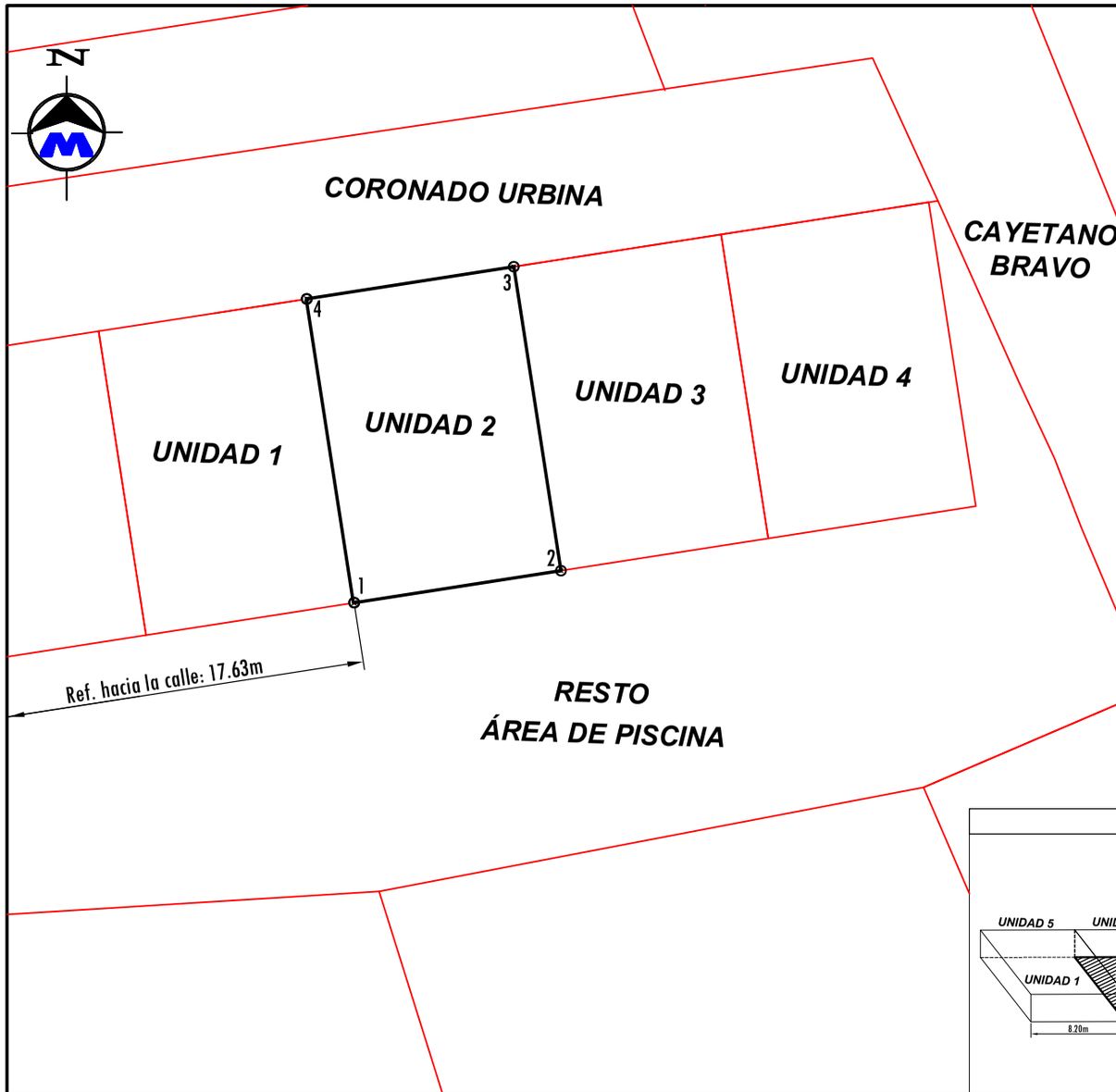

DEPARTAMENTO DE GRANADA MUNICIPIO DE GRANADA

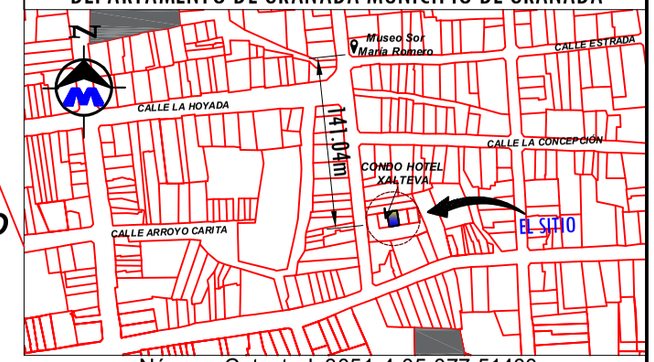

Número Catastral: 3051-4-05-077-51400
Planta de Ubicación Sin Escala

COORDENADAS NO VINCULADAS A LA RED GEODESICA DE NICARAGUA

CUADRO DE CONSTRUCCION

LADO EST	LADO PV	RUMBO	DISTANCIA	V	COORDENADAS Y	COORDENADAS X
				1	1,318,664.9538	613,432.8207
1	2	N 81°09'50.00" E	8.200	2	1,318,666.2134	613,440.9234
2	3	N 08°50'10.00" W	12.014	3	1,318,678.0843	613,439.0780
3	4	S 81°09'50.00" W	8.200	4	1,318,676.8247	613,430.9753
4	1	S 08°50'10.00" E	12.014	1	1,318,664.9538	613,432.8207

SUPERFICIE: 98.511 m2 = 139.73 Vrs2

ESQUEMA DE UBICACIÓN

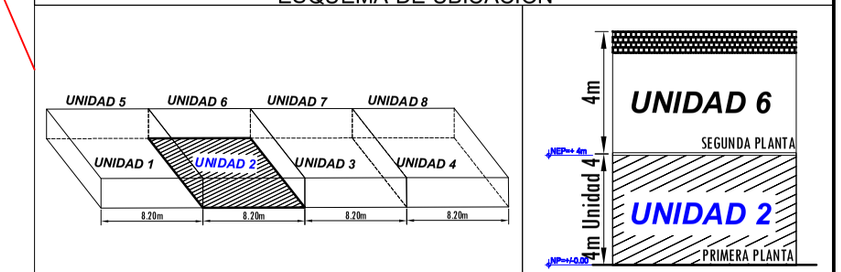

Objeto Lev: Desmembración	Número Catastral: 3051-4-05-077-51400	FIRMA:
Enajenante: DONALD JAY SNYDER Pasaporte USA: 521499712	Ubicación: Casa Museo Sor María Romero 141.04 m SE, Condominio Hotel Xalteva. Unidad 2. Municipio de Granada, Departamento de Granada.	Ejecuta: Ing.Bosco Javier Morgan Lic. Catastral: BMM100426 Cel: 8883-7568 Email: ingmorgan73@gmail.com
Adquirentes: SCOTT ANDREW HOROWITZ Pasaporte: 583132846 ANA HOROWITZ Pasaporte: A34627863	Área: 98.511 m² = 139.73 Vrs² — Escala: 1 / 250	Fecha: 28 de Mayo del 2025

ESPACIO PARA ESQUELA