MORGAN
CONSTRUCCIONES

Diseño – Construcción- Topografía
Iglesia de Xalteva 4c al sur
½ c al Este. Granada, Nicaragua.
Email: ingmorgan73@gmail.com
Ruc: 201-050273-0002A.
Lic. MTI 5365. Lic. Catastral BMM100426
www.morganconstrucciones.com
Celular: 8883-7568

INFORME DE LEVANTAMIENTO TOPOGRÁFICO

DE LAS PARCELAS IDENTIFICADAS CON EL Nº CATASTRAL 63123453645020 Y 63123440911420.

PROPIETARIO: CARGILL DE NICARAGUA SOCIEDAD ANÓNIMA **FECHA: 15 DE MAYO DE 2025**

RUC Nº J0310000003203

UBICACIÓN: COMARCA LOS MALACOS. MUNICIPIO DE GRANADA, DEPARTAMENTO DE GRANADA.

ELABORADO POR: ING. BOSCO JAVIER MORGAN
LIC. CATASTRAL: BMM100426

<u>PARCELA No 1</u>
(Parcela Norte)
Plano T-3ZVC7F-001
No Catastral: 63123453645020
Área del plano: 128,591.57 m² = 18.24 Mz

- **<u>Ubicación:</u>** Comarca Los Malacos, de MONISA 4,110.76 m al Norte, sobre la carretera Los Malacos. Municipio de Granada, Departamento de Granada.
- **Numero Catastral: 63123453645020**
- **<u>Propietario:</u>**

- CARGILL DE NICARAGUA SOCIEDAD ANÓNIMA, RUC Nº J0310000003203

Área Conforme a Plano aprobado: Según plano con Tran ID **T-3ZVC7F-001**, es de **128,591.57 m²,** equivalente a **18.24 Mz**

- **Colindantes**:

Norte: Berta Arguello de Lacayo

Sur: TIP-TOP INDUSTRIAL SOCIEDAD ANÓNIMA.

Este: Berta Arguello de Lacayo

Oeste: Camino a los Malacos, Finca la PORRA.

<u>PARCELA No 2</u>
(Parcela Sur)
Plano T-3ZYA7L-001
No Catastral: 63123440911420
Área del plano: 64,828.58 m² = 9.19 Mz

- **<u>Ubicación:</u>** Comarca Los Malacos, de MONISA 3,952.49 m al Norte, sobre la carretera Los Malacos. Municipio de Granada, Departamento de Granada.
- **Numero Catastral: 63123440911420**
- **<u>Propietario:</u>**

- CARGILL DE NICARAGUA SOCIEDAD ANÓNIMA, RUC Nº J0310000003203

Área Conforme a Plano aprobado: Según plano con Tran ID **T-3ZYA7L-001**, es de **64,828.58 m²,** equivalente a **9.19 Mz**

- **Colindantes**:

Norte: TIP-TOP INDUSTRIAL SOCIEDAD ANÓNIMA.

Sur: Berta Arguello de Lacayo

Este: Berta Arguello de Lacayo

Oeste: Camino a los Malacos, Finca la PORRA.

Los cuales la sumatoria de los planos aprobados de la **parcela número uno** y la **parcela número dos** descritas en el presente informe hace un área total de **193,420.15 m²,** equivalente a **27.43 Mz.**

LEVANTAMIENTO TOPOGRÁFICO ACTUAL

Conforme a levantamiento catastral efectuada en la fecha 14 de Mayo del 2025, realizado con un equipo GNSS ALFA PLUS, obteniendo las coordenadas de cada vértice del polígono. Se tomó las medidas del perímetro de ambas parcelas de manera global, el cual físicamente se verificó que posee un área total de 191,788.958 m², equivalente a 27.21 Mz, esto difiere respecto a la sumatoria de los planos aprobados detallado en el presente informe (área total de los planos aprobados T-3ZVC7F-001 y T-3ZYA7L-001 es de 193,420.15 m², equivalente a 27.43 Mz.), habiendo una diferencia a menor de 1,631.192 m². Esta diferencia es debido a errores angulares, lineales y de desplazamiento en comparación con el plano aprobado.

Se recomienda someter aprobación de nuevos planos topográficos, para subsanar los errores anteriores y así mismo extender la vigencia de los planos.

Sin mas a que referirme les saludo, dado en la ciudad de Granada a los 15

días del mes de mayo del 2025.

Atentamente:

_____

Ing. Bosco Javier Morgan
Morgan-Construcciones
LIC. MTI:5365
LIC. CATASTRAL: BMM100426

ANEXOS

PARCELA No 1
(Parcela Norte)
Plano T-3ZVC7F-001
No Catastral: 63123453645020
Área del plano: 128,591.57 m² = 18.24 Mz

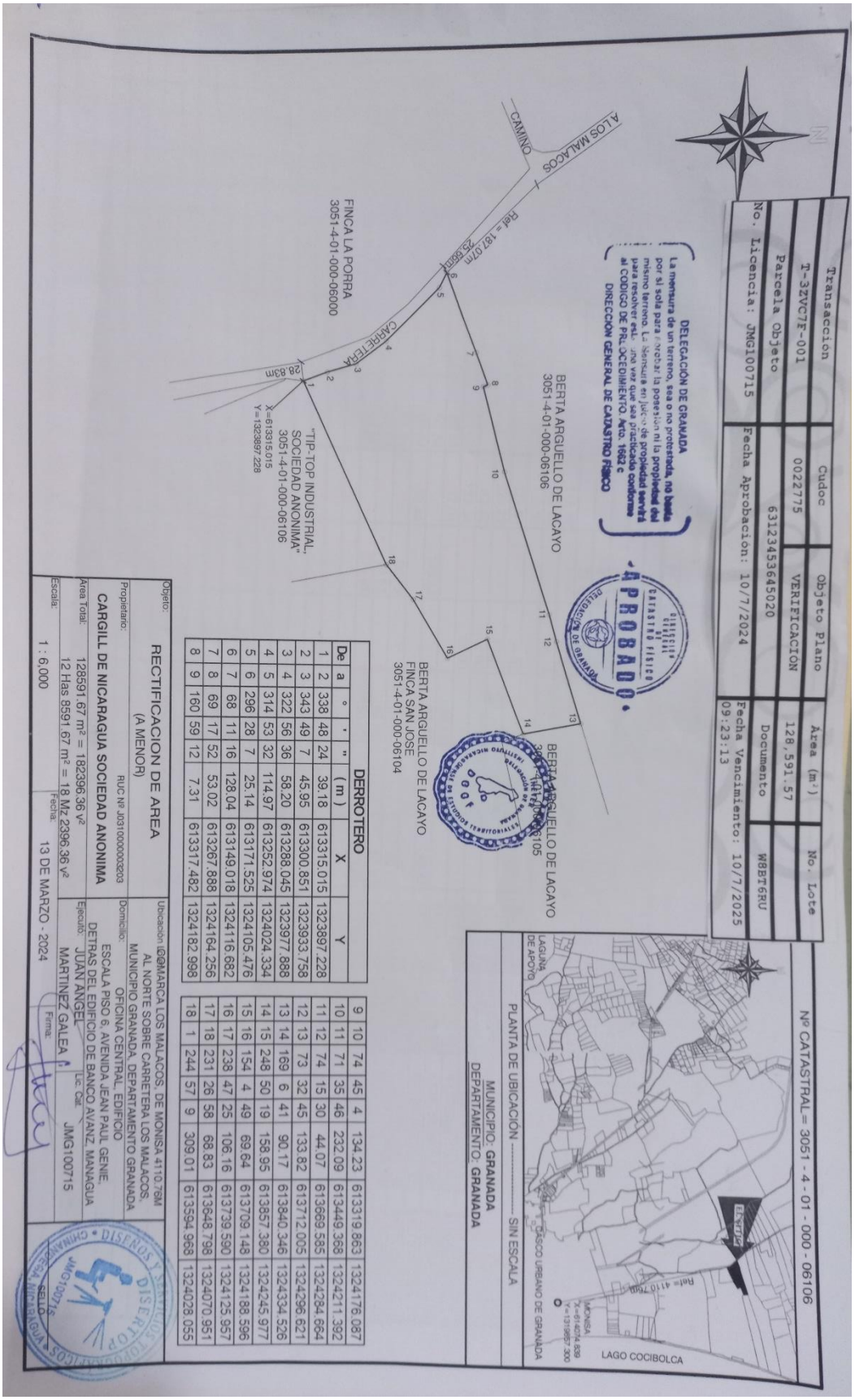

PARCELA No 2
(Parcela Sur)
Plano T-3ZYA7L-001
No Catastral: 63123440911420
Área del plano: 64,828.58 m² = 9.19 Mz

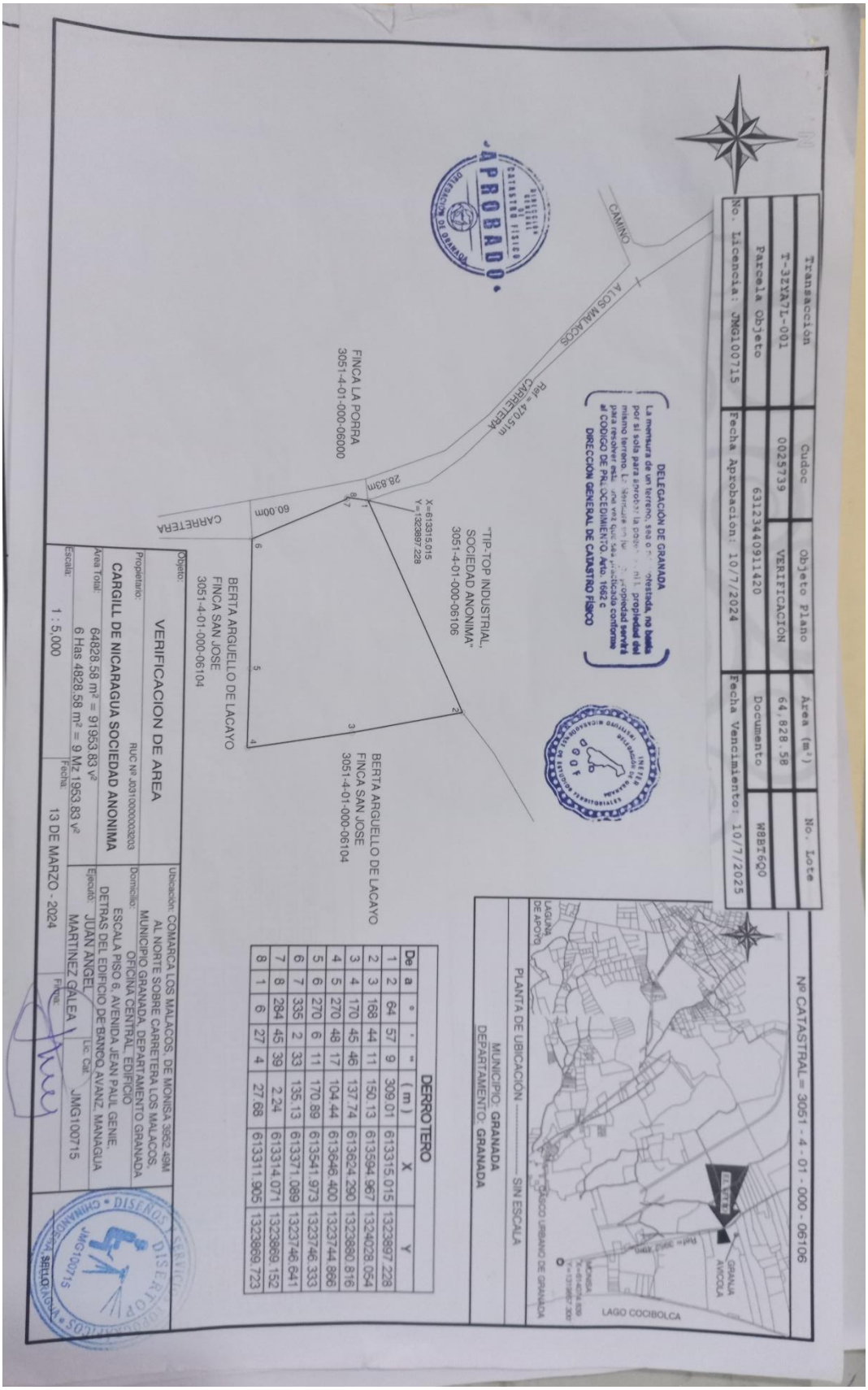

LEYENDA

_____ **Perímetro de planos aprobados**
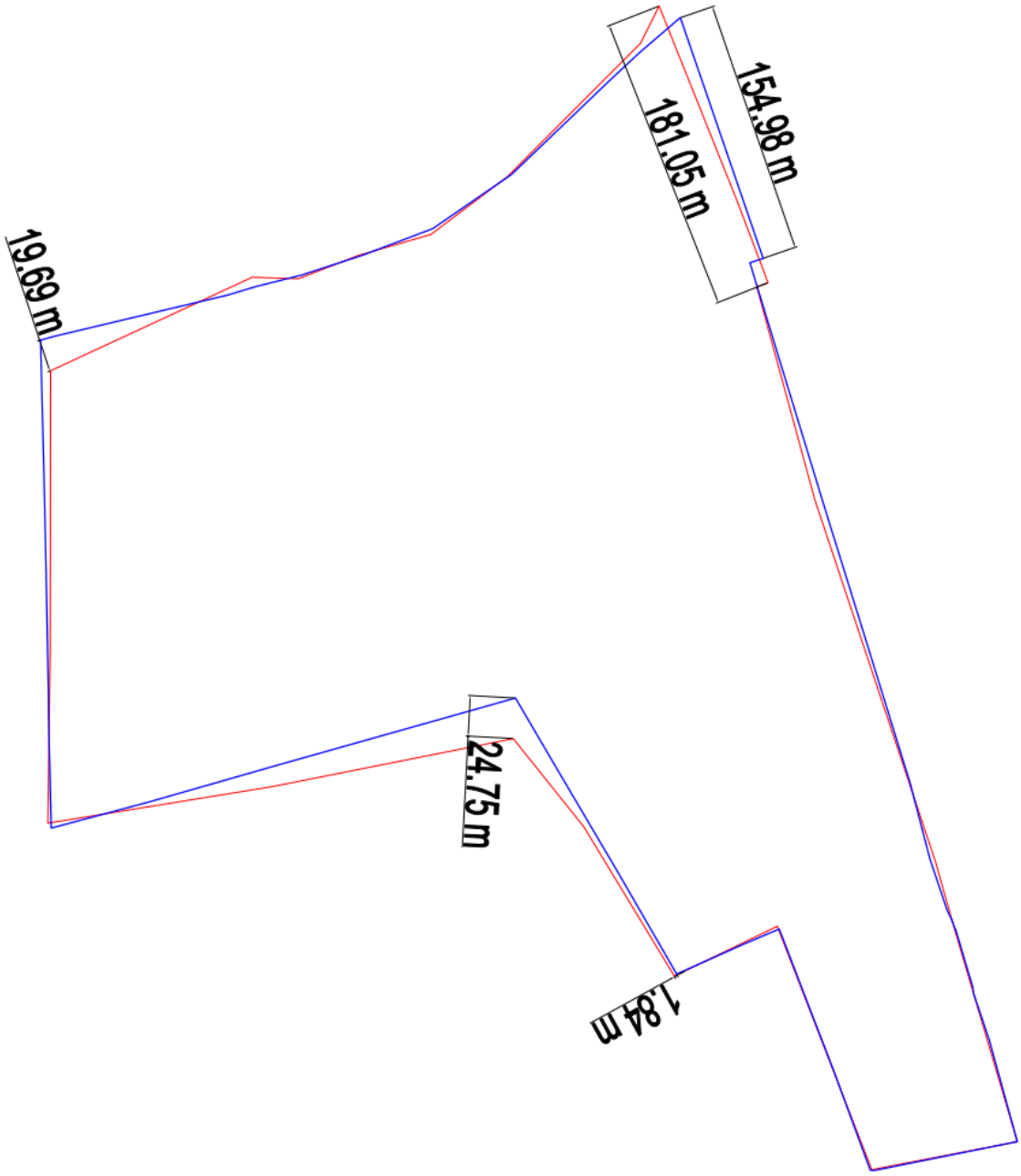
_____ **Perímetro de levantamiento topográfico realizado**