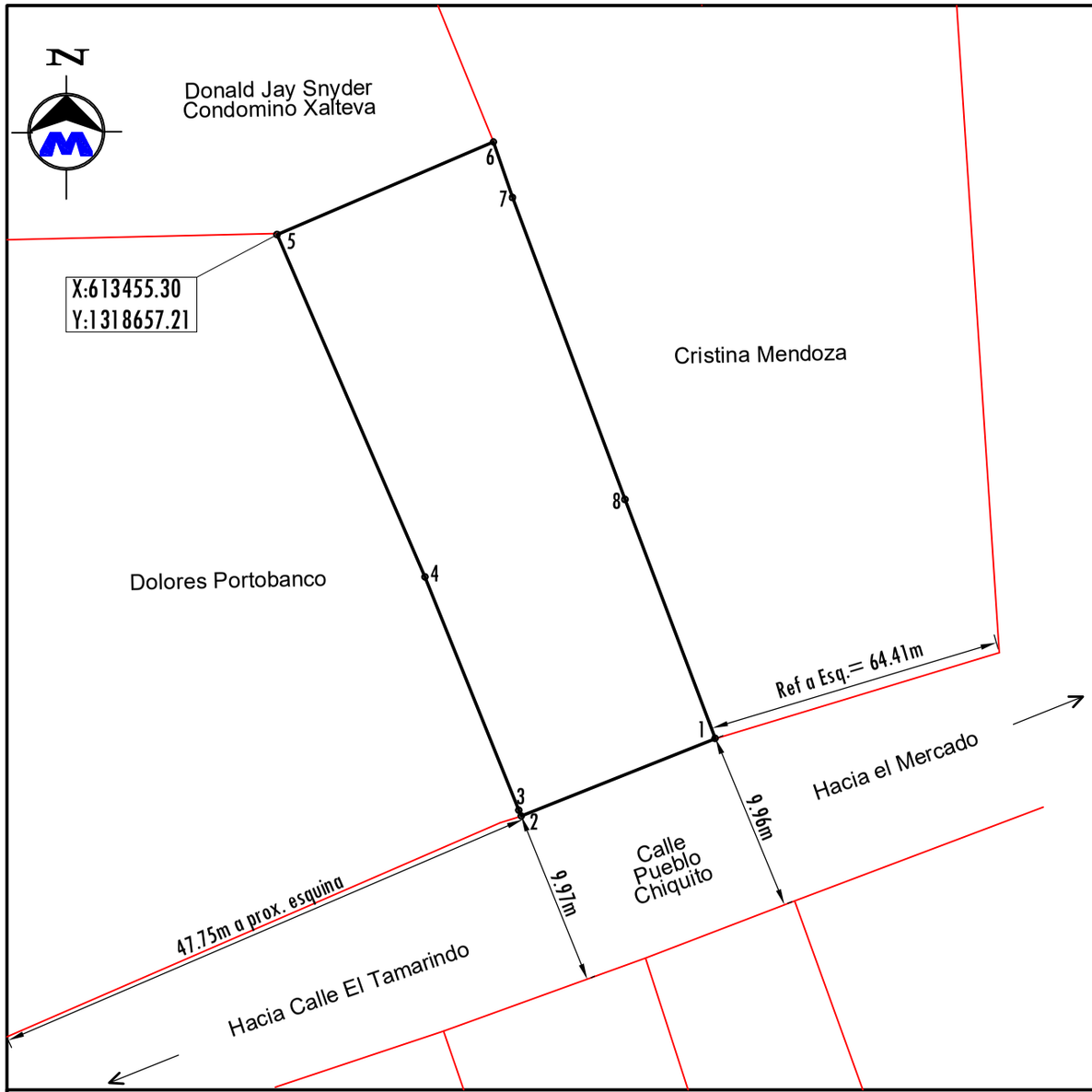

DEPARTAMENTO DE GRANADA MUNICIPIO DE GRANADA

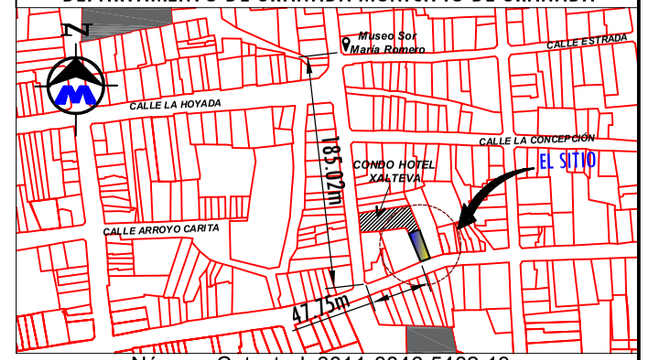

Número Catastral: 6311-3846-5482-13
Planta de Ubicación Sin Escala

Esquema de Ubicación

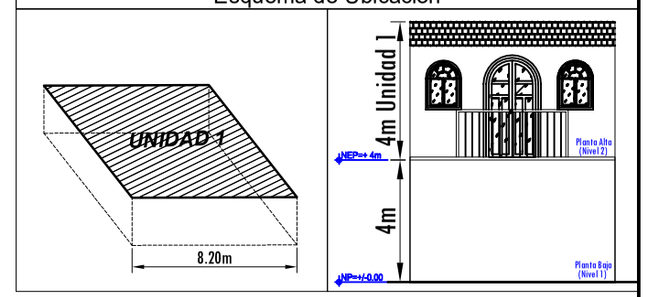

COORDENADAS NO VINCULADAS A LA RED GEODESICA DE NICARAGUA

DERROTERO

LÍNEA	RUMBO	DIST	COORD UTM
1-2	S68°15'02"W	8.20	16P 613472.50, 1318637.41
2-3	N21°22'14"W	0.25	16P 613464.88, 1318634.37
3-4	N21°53'15"W	9.87	16P 613464.79, 1318634.60
4-5	N23°21'46"W	14.65	16P 613461.11, 1318643.76
5-6	N66°52'29"E	9.24	16P 613455.30, 1318657.21
6-7	S18°44'59"E	2.30	16P 613463.80, 1318660.84
7-8	S20°27'19"E	12.65	16P 613464.54, 1318658.66
8-1	S20°38'10"E	10.04	16P 613468.96, 1318646.81

Área: 214.0005 m²=303.5415 Vrs²

Objeto Lev: Constitución de Régimen Horizontal (PH)	Numero Catastral: 6311-3846-5482-13		FIRMA:
Propietario: Donald Jay Snyder Pasaporte USA: 521499712	Ubicacion: Casa Museo Sor María Romero 185.02 m SE, 47.75 m al Este, Condominio Hotel Xalteva, M/I. Municipio de Granada, Departamento de Granada.		Ejecuta: Ing.Bosco Javier Morgan Lic. Catastral: BMM100426 Cel: 8883-7568 Email: ingmorgan73@gmail.com
Área: 214.0005 m²=303.5415 Vrs²	Escala: 1 / 250	Factor de Escala: 1.418415	Fecha: 29 de Abril del 2025

ESPACIO PARA ESQUELA